Visor Geológico

Transforma tus datos en decisiones. Una plataforma integral para la validación, visualización y análisis de campañas de sondajes, diseñada para la precisión técnica y la eficiencia operativa.

01. Visualización Multidimensional

Entorno 3D integral de alto rendimiento

INTEGRACIÓN DE TIPOS DE DATOS

- **Sondajes:** Trazas con codificación dinámica por ley o litología. Control de espesores y etiquetas.
- **Modelos 3D:** Carga de cuerpos mineralizados con transparencia en tiempo real para análisis espacial.
- **Topografía:** Importación de superficies para contextualizar datos de exploración.



POTENCIA VISUAL

Navegación Fluida

Visor Geológico integra topografía, trazas de sondajes y controles de navegación avanzados en una sola escena de alto desempeño.

Ideal para validar la relación espacial entre perforaciones y volúmenes interpretados en tiempo real.

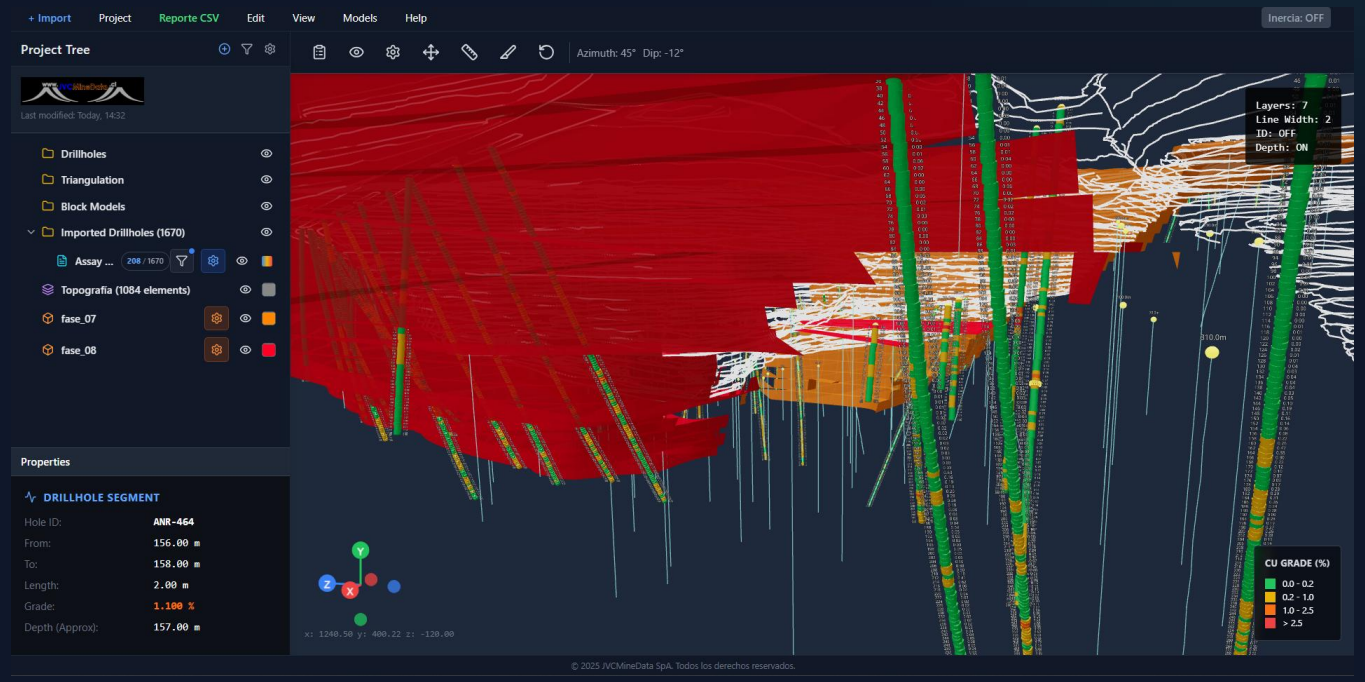

02. Inteligencia de Carga y Validación

Garantía de integridad referencial y lógica

VALIDACIONES AUTOMÁTICAS

Integridad

Verifica que cada registro en Assay y Survey tenga su correspondiente entrada en el archivo Collar.

Profundidad

Detecta errores lógicos como intervalos invertidos (From > To) o profundidades que exceden el largo total.

Consistencia

Alerta inmediata sobre sondajes duplicados o coordenadas inconsistentes entre archivos.

ASISTENTE INTELIGENTE

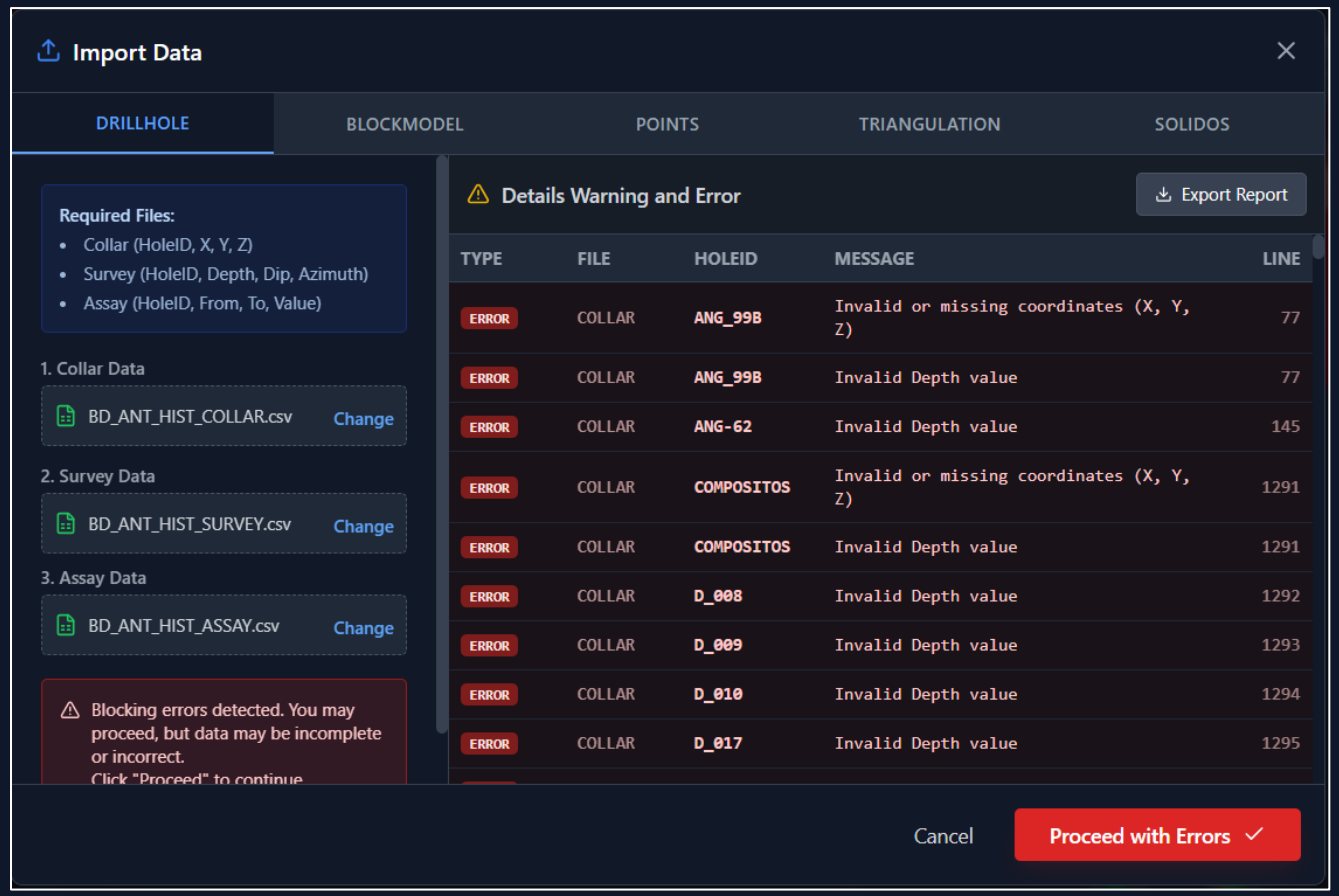

Análisis en Tiempo Real

Nuestro motor analiza los CSVs antes de cargarlos al motor 3D. El panel de **"Details Warning and Error"** permite corregir inconsistencias antes de iniciar el análisis.

Olvídate de los errores silenciosos que comprometen tus modelos geológicos.

03. Análisis y Reportabilidad

Datos precisos para estimación de recursos

ANÁLISIS DE INTERSECCIONES (SOLID INTERSECT)

Reporte de Intersecciones
Analizar sondajes que intersectan sólidos

Seleccionar Sólido Objetivo

fase_07

Generar Reporte

HOLE ID	FROM	TO	LENGTH	TYPE	GRADE
ANH-225	0.00	2.00	2.00	INSIDE	0.200
ANH-225	2.00	4.00	2.00	INSIDE	0.250
ANH-225	4.00	6.00	2.00	INSIDE	0.170
ANH-225	6.00	8.00	2.00	INSIDE	0.220
ANH-225	8.00	10.00	2.00	INSIDE	0.170
ANH-225	10.00	12.00	2.00	INSIDE	0.270
ANH-225	12.00	14.00	2.00	INSIDE	0.240
ANH-225	14.00	16.00	2.00	INSIDE	0.340
ANH-225	16.00	18.00	2.00	INSIDE	0.210
ANH-225	18.00	20.00	2.00	CROSS	0.210
ANH-227	0.00	2.00	2.00	INSIDE	0.290

Total encontrados: **540** tramos

Descargar CSV

Algoritmo Preciso

Determina puntos exactos de entrada y salida (From/To) de cada sondaje en el cuerpo mineralizado.

Distingue entre tramos que cruzan (CROSS) y tramos contenidos (INSIDE).

Asocia la ley mineral (grade) del tramo interceptado

HERRAMIENTAS DE CONTROL GEOLÓGICO

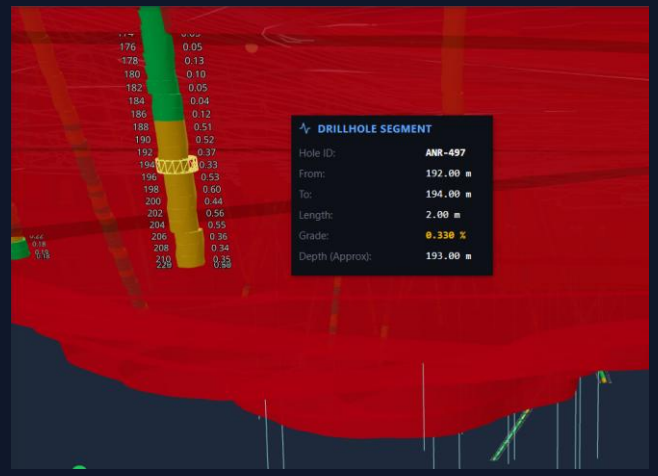

Inspector

Detalle por tramo: Ley, profundidad y tramos al instante.

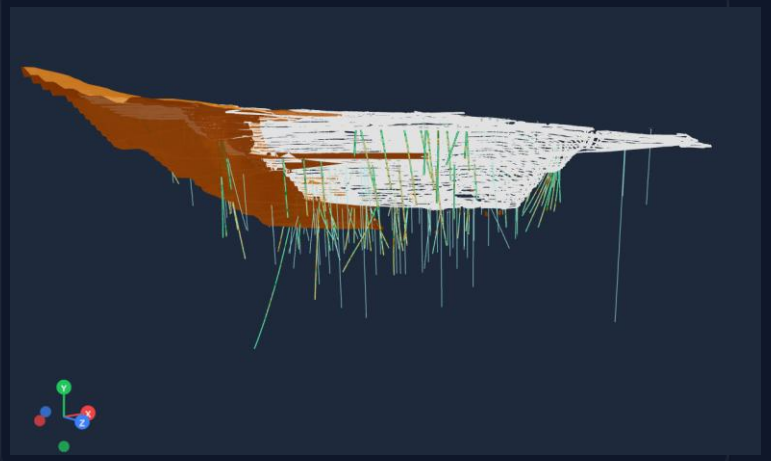

Filtros

Aísla datos por proyecto, fecha o rango de leyes dinámicamente.

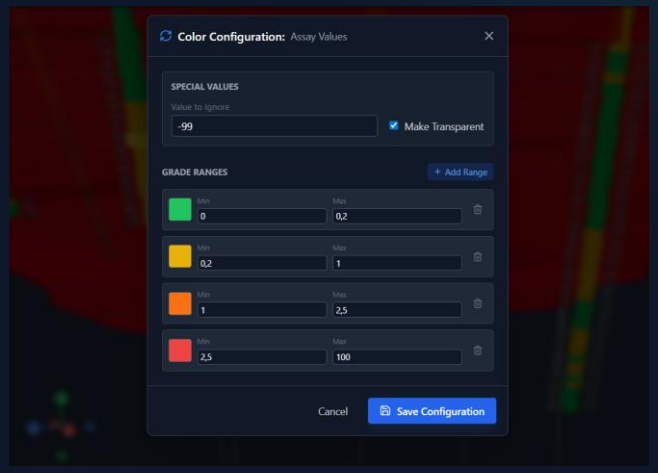

Configuración

Escalas de color y etiquetas personalizadas para reportes.

EFICIENCIA EN VALIDACIÓN DE CAMPAÑAS

Ahorro del 92% en tiempo de validación técnica, permitiendo un análisis geológico más profundo.

¿Preguntas?

Confianza en sus datos, velocidad en su operación.

Visor Geológico

www.JVCMineData.cl

Jorge@jvcminedata.cl